Echange sur découverte d’un nouveau site en montagne.

ex traité: st andré
Même méthode utilisée à Samoëns/Mieussy

Attention, ma méthode perso (surtout sur les flips 4 et 7).

N’hésitez pas à partager la votre durant toute la présentation, sans attendre la fin. J’espère que de cet échange naitront nos progrès a tous.

Les sommets environnants

Le plus détaillé ce sont les cartes IGN. Or c'est payant, sauf la: https://parapente.ffvl.fr/cfd/selectionner-les-vols

1- préciser les critères – il suffit de mettre le lieu (saint-andré)

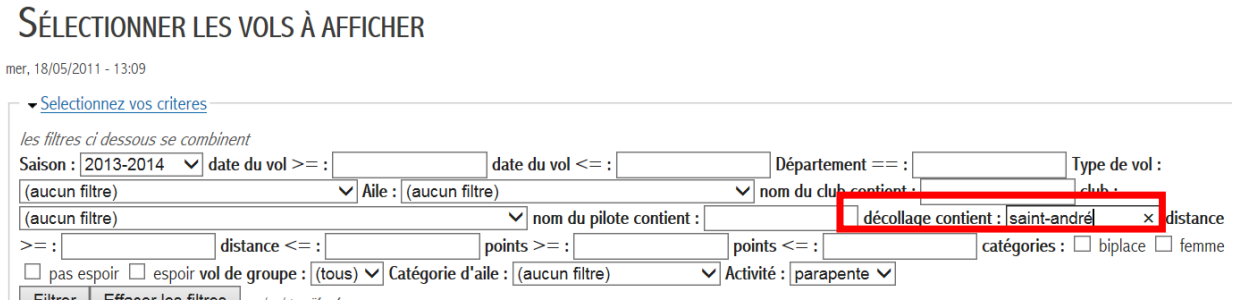

2- Choisir un vol

3- Choisir la carte « France » - cartes IGN

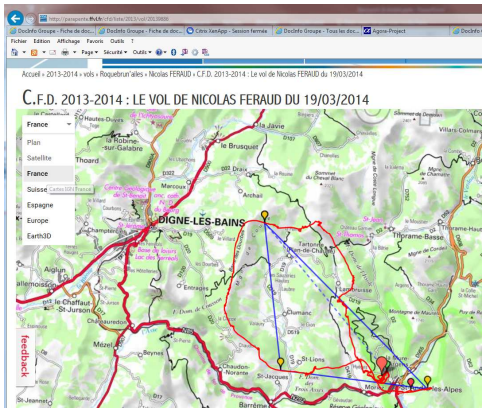

Zoomer pour voir les details: nom des sommets , altitudes, courbes de niveaux

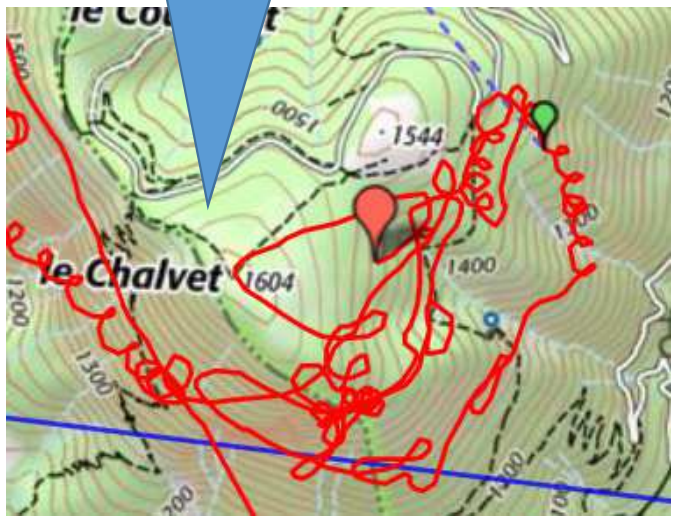

Analyse des Brises

Dans la journée, les brises de vallée remontent les vallées – à l'inverse des cours d'eau.
Vu que trouver une carte des brises n'est pas toujours possible, alors rechercher celle des cours d'eau, sur les sites de peche par exemple

http://www.achigan.net/spot.php?tag=Alpes-de-Haute-Provence+%2804%29

Dommage qu'il n'y ait pas ceci pour le 04:

https://paragliding.rocktheoutdoor.com/conseils/le-phenomene-des-brises-de-vallees/

Permet de se faire une idée et de placer les sommet et les brises de la région

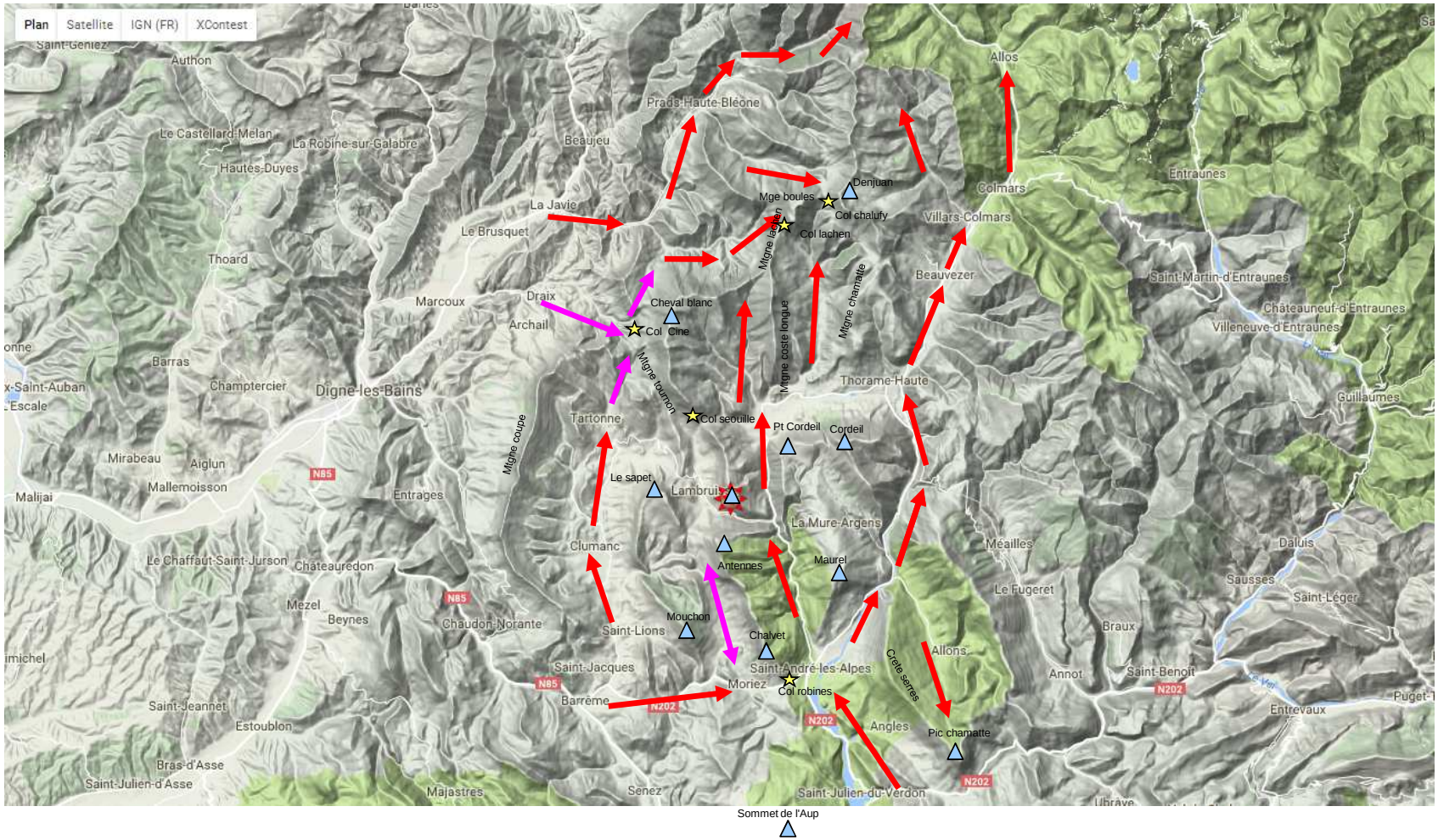

Rester humble: a discuter avec des locaux, d'autres pilotes connaissant bien, l'ecole ….

Les circuits

1- circuits proposés par les écoles, clubs ….

http://www.aerogliss.com/cross-faciles/*

Une page d'erreurs, quelle horreur

Mais en regardant de plus près:

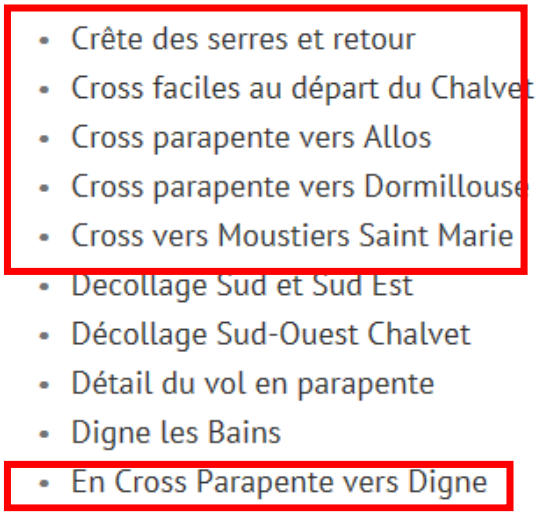

https://www.flystandre.com/single-post/Saint-Andre-Les-Alpes-XC-Inspiration

Les circuits

2- circuits déjà réalisés

Explorer ceux déjà réalisés sur la région: via le site de la CFD - Etre réaliste – **placer la catégorie de son aile**

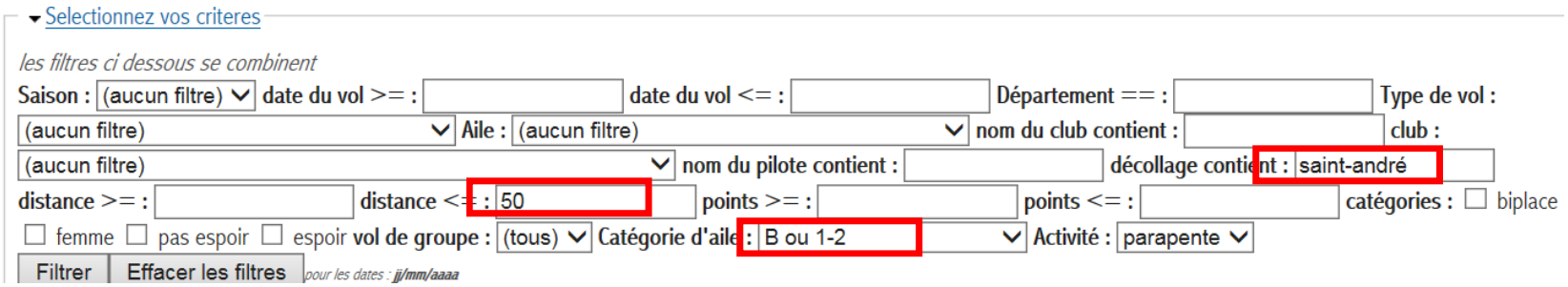

Ex:
A: Alpha 5, KOYOT, PAWN
B: EPSYLON, HOOK, LEAF
C SIGMA, IKUMA

Plus facile désormais quand on connait le nom des sommets

En plaçant le curseur dans la coupe du dessous, la position sur le tracé se met a jour, ainsi que les mesures du cadre vert:
Permet d'analyser les tracés, connaitre des hauteurs de départ
Avec un peu d'observation, de connaitre le sens des brises
ce jour/heure la: via la vitesse sol dans le rectangle vert

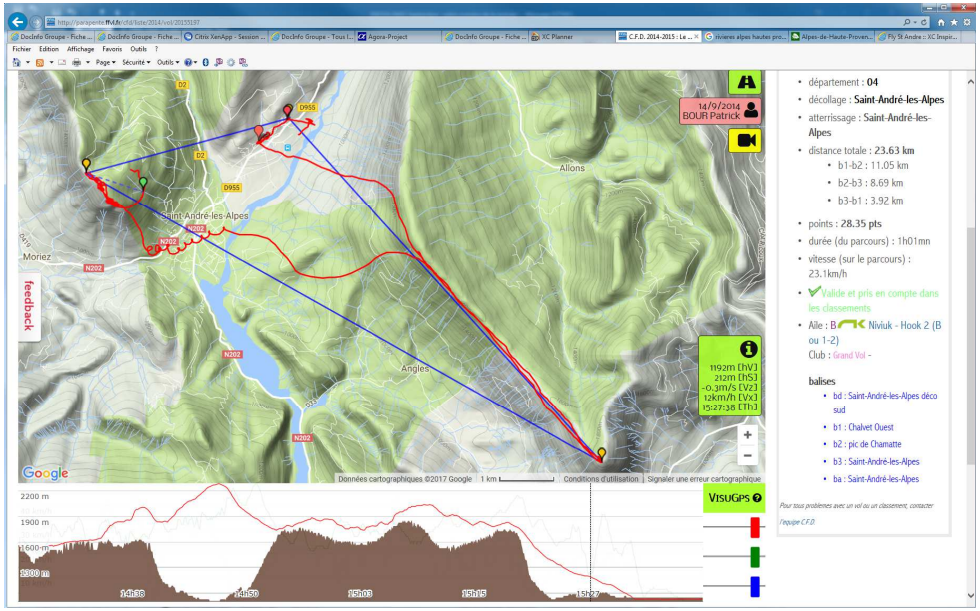

Possible alors de se faire une idée des hauteurs nécessaires d'après ces traces –

Sans certitude, cela dépend de beaucoup de paramètres, c'est un ordre de grandeur
Garder en tête qu'il faudra ensuite ajouter des marges car ceux qui ont réalisé ces vols sont plus expérimentés

	A	B	C	D	E	F	G	H
1								
2								
3								
4	Départ	Hauteur sol (m)	Hauteur Départ (m)	Gain mini	Arrivée	Hauteur Arrivée (m)	Conditions	Commentaire
5								
6	Chalvet	1600	2300	700	Crete serres face ouest (Haut)	1500	calmes apres midi	ideal sans vent meteo, rien que les brises
7	Chalvet	1600	2600	1000	Crete serres face ouest (Haut)	1800	calmes apres midi	ideal sans vent meteo, rien que les brises
8	Crete serres face ouest (Haut)	1800	1800	0	Aérogliss	900	calmes apres midi	si contré, aller poser a la Mure
9								
10	Chalvet	1600	2100	500	Maurel face sud (Bas)	1400	Matin Brises montante	un peu de barreau pour contrer la brise (composante, pas de face)
11	Maurel	1770	1720	-50	Face sud Chalvet sous deco sud	1320	Matin Brises montante	un peu de barreau pour contrer la brise (composante, pas de face)
12	Chalvet	1600	1800	200	Vers montagne de l'aulp			
13								
14	Chalvet	1600	1600		Antennes		Vent SW 15 km/h	tout droit en suivant crete
15	Chalvet	1600	1600		Antennes		Vent SW 15 km/h	tout droit en suivant crete
16								
17	Barre chalvet sommet N	1800	1800	0	Sommet de meurier(Lambruisse)(bas)		Vent W 10km/h ou SW 15 km/h	
18								
19								
20	Sommet de meurier(Lambruisse)	1742	3000	1258	Cheval Blanc (sommet)	2300		
21	Sommet de meurier(Lambruisse)	1742	1900	158	sommet de seoulne face S	1720		
22	Sommet de meurier(Lambruisse)	1742	1950	208	Barre chalvet sommet N	1650	Vent W 10km/h	simul
23								
24	Sommet de seoulne	1800	1850	50	montagne de tournon (bas)	1715	Vent W 10km/h ou SW 15 km/h	Passer le col sous le sommet a 1800m – monter avec le th sur arete proche col de seoulne pour W 10km/h – sans souci en
25								
26	Sommet montagne tournon	2050	2050	0	sapet face W (bas)	1520	Vent W 10km/h	simul:
27	Sommet montagne tournon	2050	2470	420	Mouchon face W angle N (bas)	1350	Vent W 10km/h	simul:
28								
29	Sommet Cheval Blanc	2300	2500	200	sapet face W (bas)	1330	Vent SW 15 km/h	avec barreau
30								
31	Mouchon	1600	1530	-70	Chalvet face W (Bas)	1230	Vent W 10km/h ou SW 15 km/h	
32								

Les circuits

3- se construire un, quelques, objectifs persos: être réaliste, mais prévoir le cran du dessus au cas ou:

https://xcplanner.appspot.com/

https://xcplanner.appspot.com/?l=free&p=ywkkGyspf%40kgHzqDhxHi%7DE%7CsA%7DpC&s=19.0&a=0

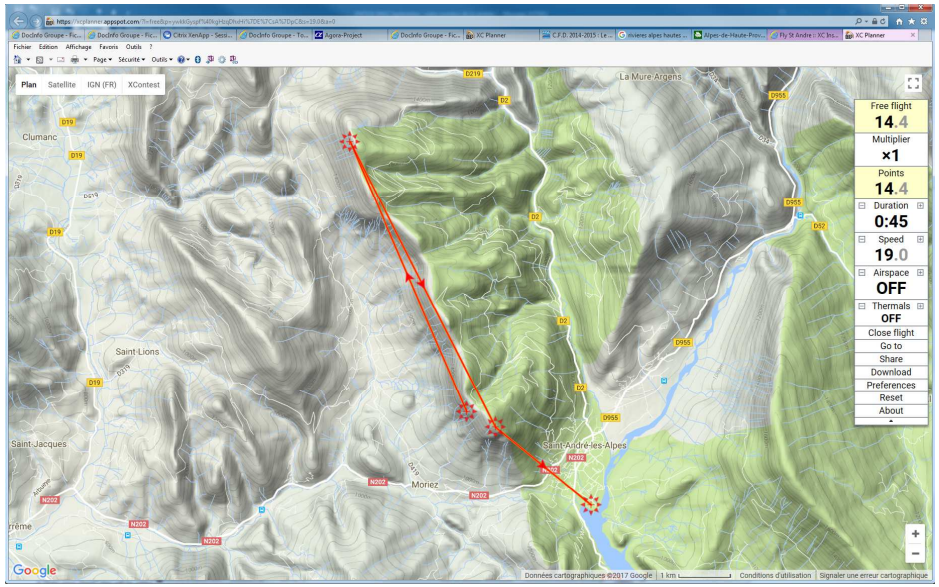

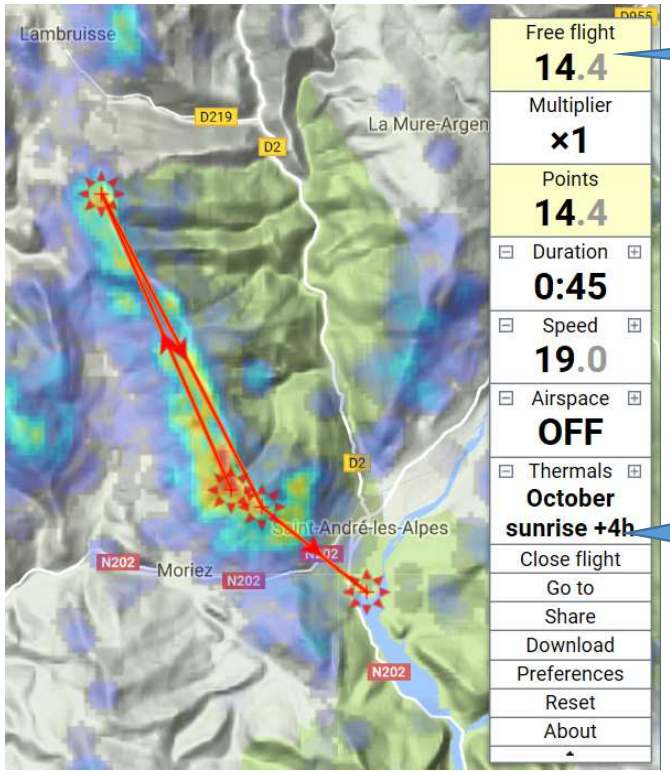

Distance

Emplacement des th – coloration sur la carte

Les circuits (à l’étranger ou même en France)

http://www.paraglidingforum.com/leonardo/tracks/world/alltimes/

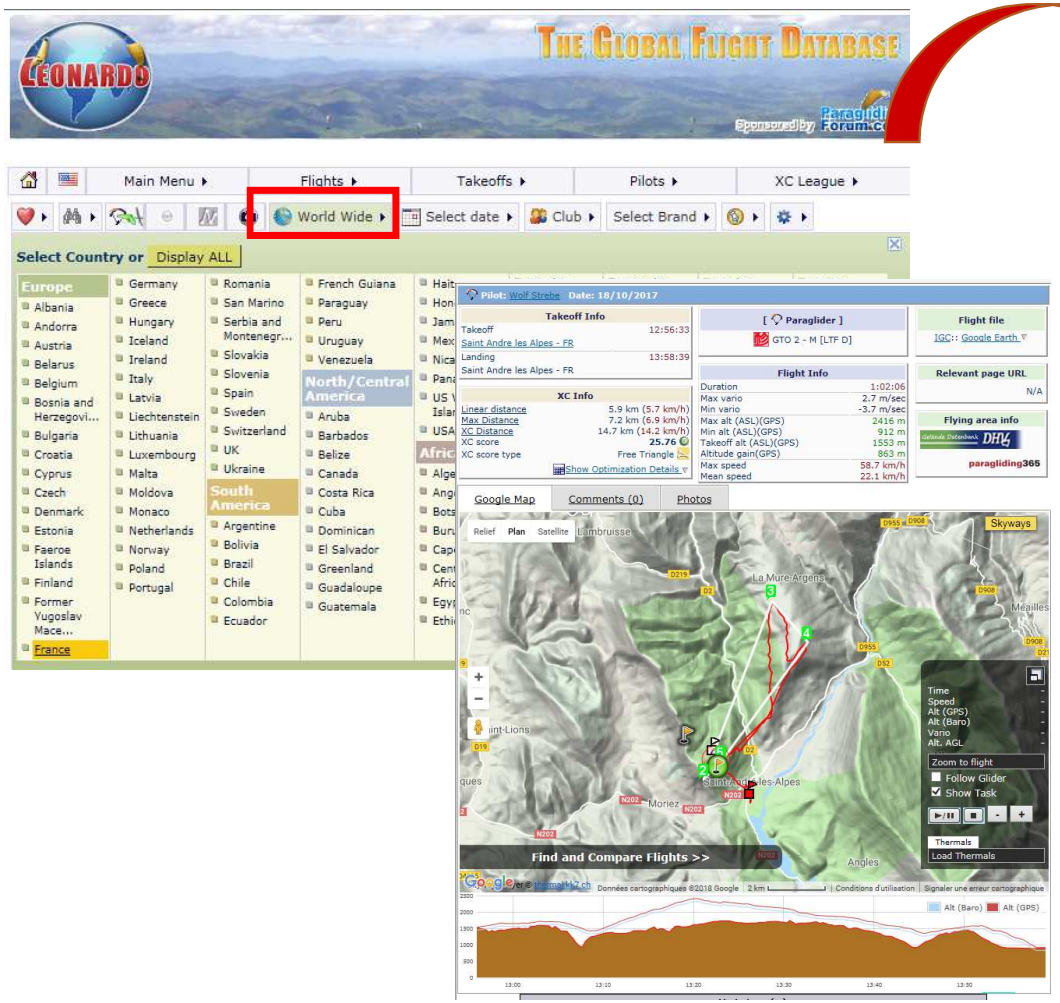

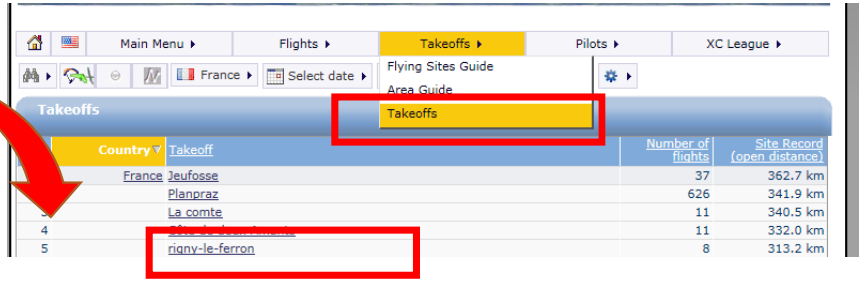

Les circuits

4- ya plus qu'a ? **Ben Non** La sécurité alors:

Prévoir les vaches sur le trajet bien sur.

https://www.google.fr/maps/@43.9139077,6.4782177,3133a,35y,353.49h,65.72t/data=!3m1!1e3

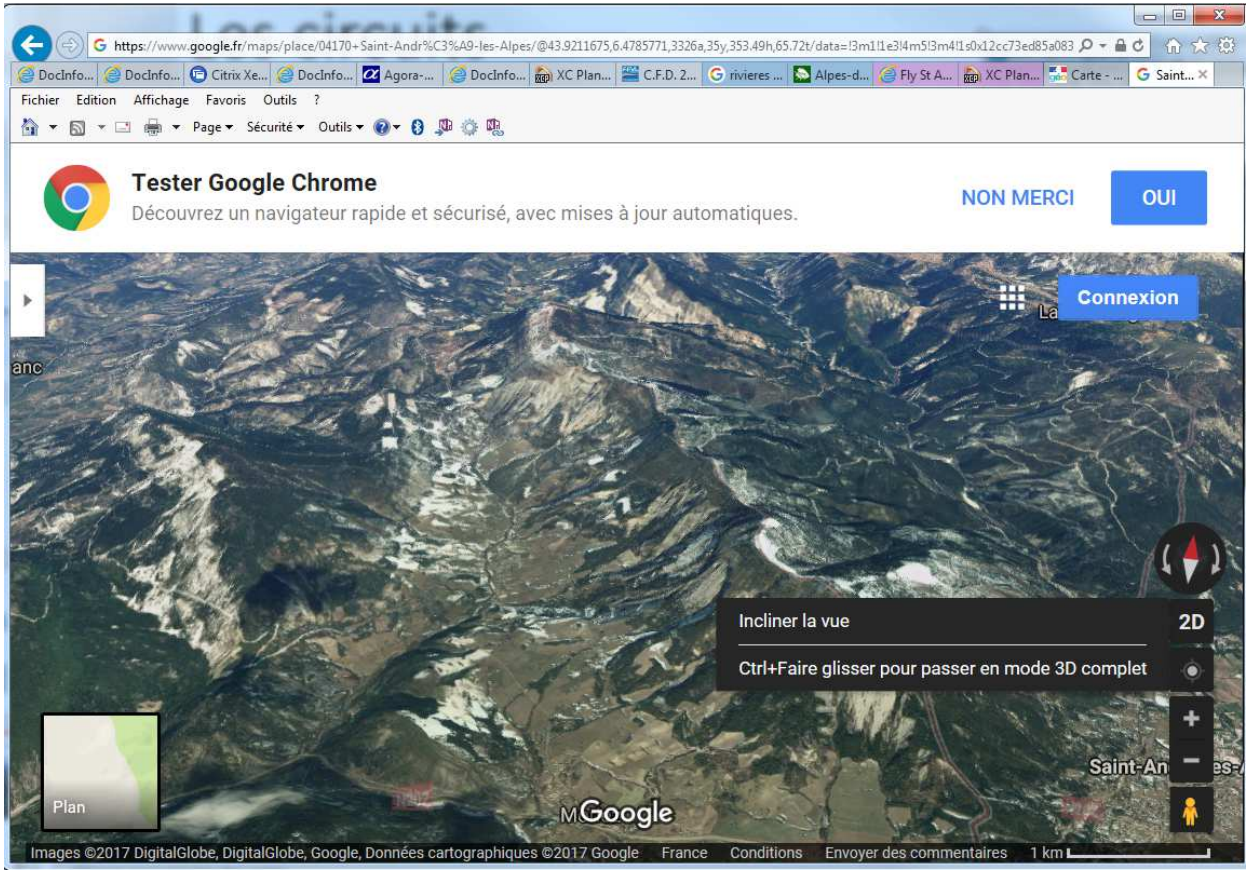

En parler avec les locaux, les écoles, les expérimentés du club pour identifier les difficultés

Liens Utiles

Notre site web: une mine d'informations

http://www.lesailesdesenart.com/index.php/voler/preparer-un-vol-outils-meteo-previs

La METEO: évidement

https://www.velivole.fr/

http://www.lesailesdesenart.com/index.php/liens

Les sites FFVL: sauf pour les « pros », permet de bien réviser les basiques

https://parapente.ffvl.fr/cfd/preparer-votre-futur-vol

http://www.efvl.fr/supports_peda_ecoles

Les instruments: évidement, si on découvre la région, penser a charger les cartes

http://www.lesailesdesenart.com/index.php/liens

Etc ……

Simulateur

Possibilité de se balader dans google earth comme si on était en parapente avec les thermique (placés a mon sens comme dans xcplanner, par contre l'aspect vent semble binaire, une seule direction alors que dans la vraie vie, ca peut evoluer.

Intérêt majeur: mémoriser les reliefs d'une région inconnue
Attention: ne pas croire tout ce que simule ce site une fois en l'air / garder des marges

Lien: http://paraglidinglogbook.com/simulator/

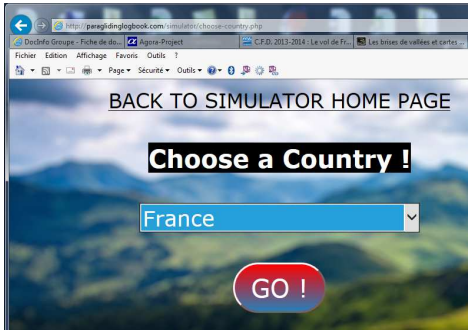

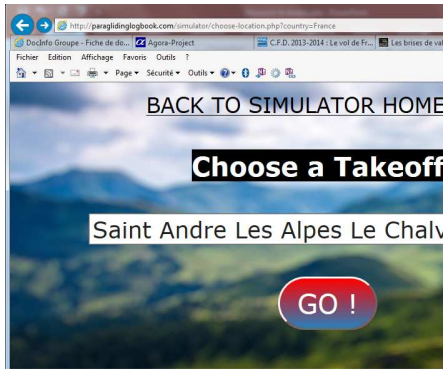

2- Saisir les parametres voulus

3- cliquer sur go …

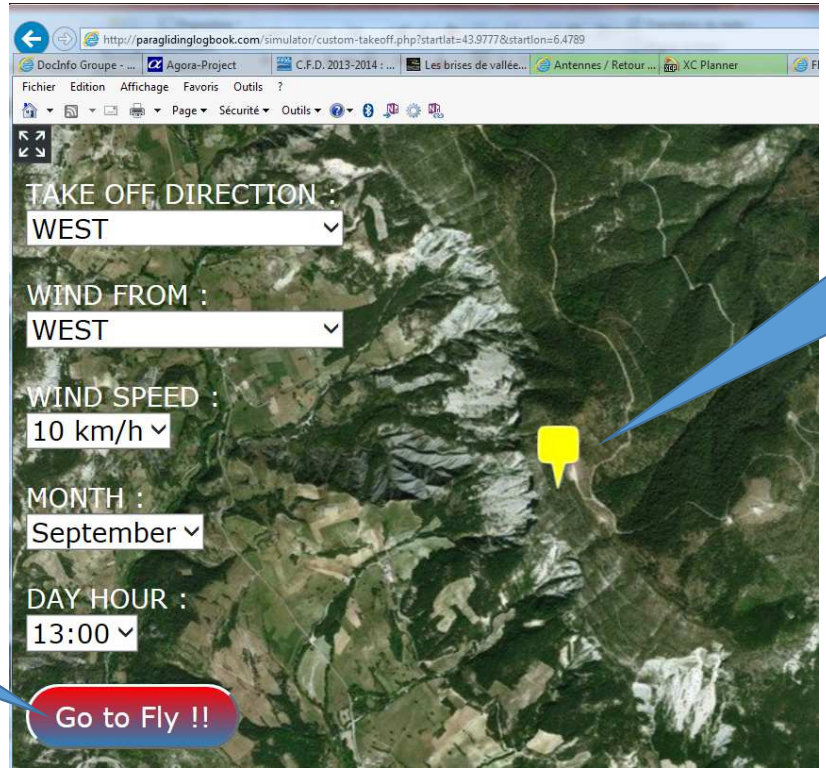

1- cliquer pour placer l'emplacement du déco si nécessaire